Groupe Représentations – Atelier d'aménagement Royan

1. Localisation et insertion du marais dans la géographie locale

Le marais de Pontaillac, situé sur la commune de Royan, dans le département de la Charente-Maritime, est un espace naturel de grande importance dans la géographie royannaise. Ce marais se trouve à proximité immédiate de l'estuaire de la Gironde, qui constitue le plus grand estuaire d'Europe. Il est également à noter que le marais de Pontaillac, localisé au sud-est de la ville de Royan, à environ 1,5 km au sud du centre-ville, et à 500 m de la plage très fréquentée de Pontaillac. Le Marais se trouve aisni à l'intersection de la zone très urbaine de la station balnéaire, et de zones périphériques, pavillonnaires et agricoles. Ce marais est en grande partie constitué de terres humides et de prairies inondables, formées par les eaux de l'estuaire de la Gironde.

Production Mehdi AMROUNE – modèle carte : Géoportail ; données : Google Earth

Le Marais de pontaillac joue ainsi un rôle essentiel dans la régulation de l'écosystème local, en servant de filtre naturel pour les eaux, en offrant un refuge pour la faune, notamment les oiseaux migrateurs, et en contribuant à la protection de la ville de Royan contre les risques de submersion marine. A ce titre, depuis 2004, la zone est classée en Zone Natura 2000, et elle bénéficie également de la protection particulière du département de la Charente Maritime, bien que ce marais ne bénéficie pas officiellement du label Espace Naturel Sensible.

Le marais de Pontaillac est ainsi étroitement lié à l'océan Atlantique et à l'estuaire de la Gironde. Ce lien se manifeste principalement par les phénomènes de marées, qui influencent le niveau de l'eau et l'écosystème du marais. Les marées hautes apportent de l'eau salée et des nutriments, favorisant la biodiversité, tandis que les marées basses permettent le développement de certaines plantes adaptées aux conditions plus sèches. Le marais joue aussi un rôle crucial en régulant les niveaux d'eau, en absorbant l'excès d'eau lors des crues et en protégeant Royan contre les risques d'inondation. De plus, il constitue une zone de transition entre les milieux marins et terrestres, abritant une faune et une flore spécifiques. Face au changement climatique, le marais de Pontaillac pourrait également devenir un refuge pour des écosystèmes menacés par la montée du niveau de la mer.

Le lien entre l'océan et le marais est essentiellement assuré par le Rivaud, un petit ruisseau reliant le marais et la plage de pontaillac. C'est ce ruisseau qui régule véritablement l'hydrologie locale en apportant de l'eau douce ou saumâtre, influence les niveaux d'eau et contribue à la fertilisation des sols par l'apport de sédiments et de nutriments. Il sert également d'habitat pour de nombreuses espèces animales et joue un rôle dans la filtration de l'eau. De plus, il aide à la gestion des risques d'inondation en évacuant l'excès d'eau vers la plage lors des fortes pluies et des marées hautes.

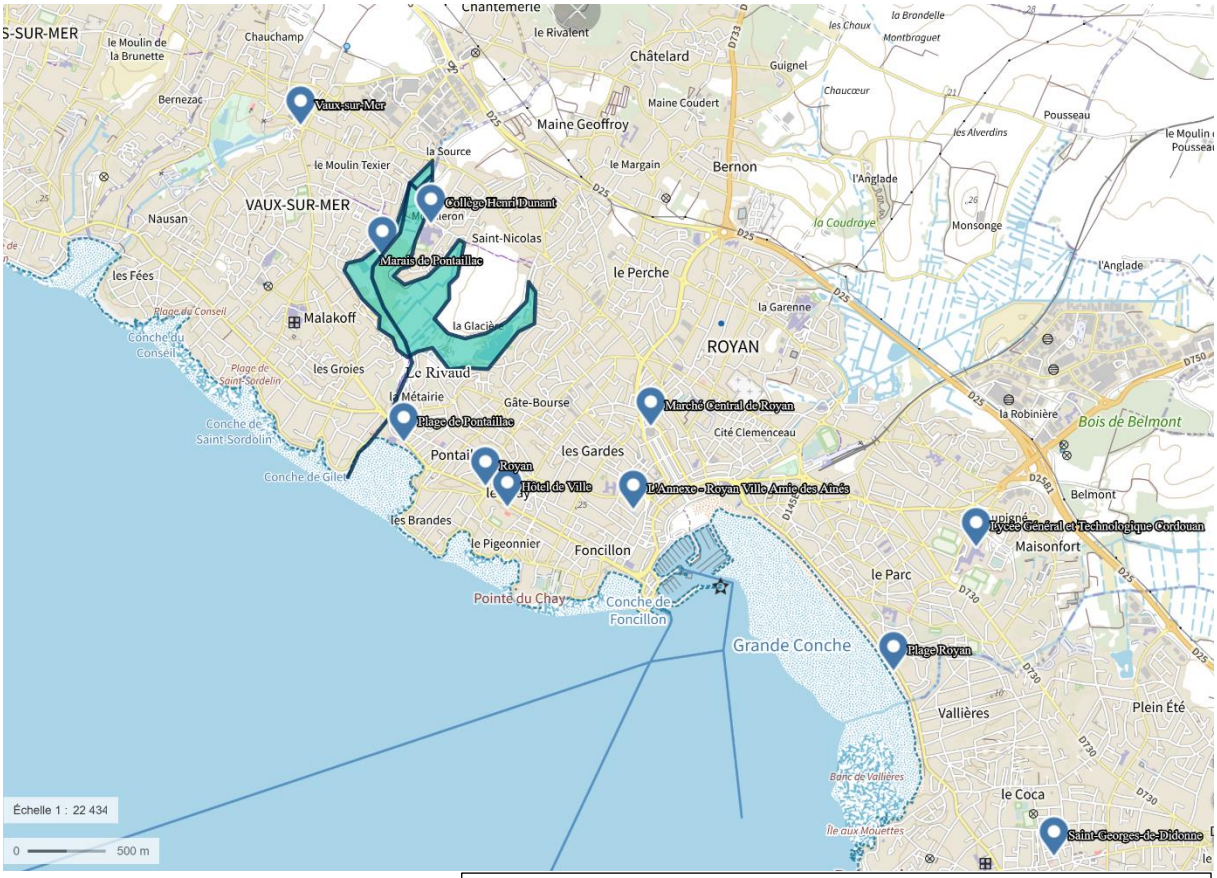

Production Mehdi AMROUNE – modèle carte : Géoportail ; données : Google Earth

En se référant aux données du Registre parcellaire de 2021, on s'aperçoit que l'activité agricole est très peu présente sur la zone du marais. Ce registre indique surtout la présence de prairies permanentes (en vert clair). En réalité il existe une part circonscrite de petites parcelles dédiées à la culture de petits potagers à vocation de consommation propre. Toutefois, à proximité du marais de Pontaillac on distingue une activité agricole non négligeable, essentiellement dédiée à l'exploitation de blé. Par ailleurs, sur le secteur saint-nicolas, où l'on a pu observer la présence de bétail, on retrouve également la présence d'une activité de fourrage (plante ou mélanges de plantes servant à l'alimentation d'animaux d'élevage).

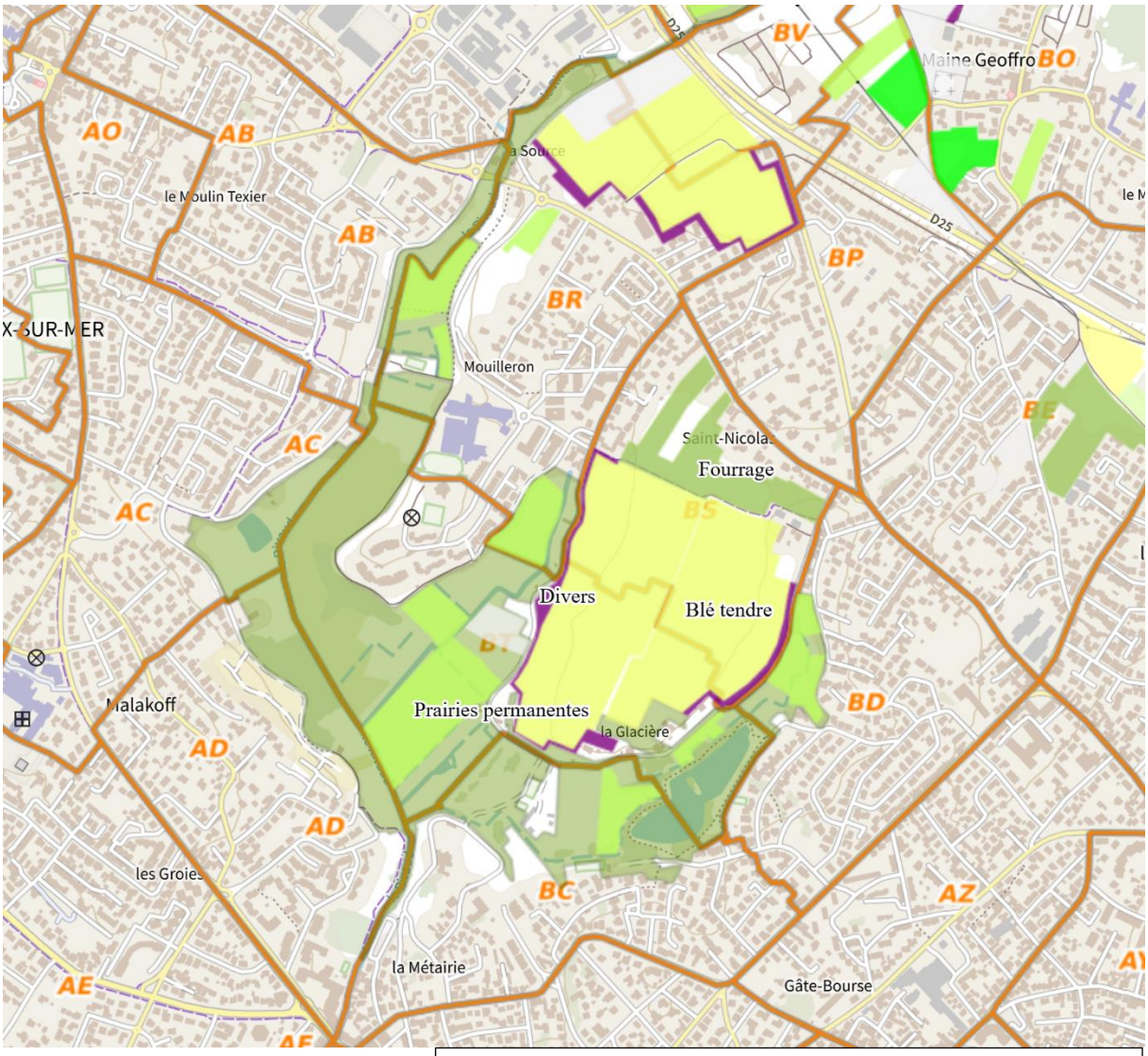

Production Mehdi AMROUNE – modèle carte : Géoportail ; données : Google Earth, Registre parcellaire

Pour ce qui est du reste des zones à proximité du marais, il s'agit essentiellement de zones constructibles, qui sont aujourd'hui très urbanisées. Cette forte tension immobilière et foncière qui n'a cessé de s'accroitre dans le quartier depuis les 30 glorieuses, dans un contexte national et local de recul de l'agriculture, entraine encore aujourd'hui une pression maximale sur les dernières parcelles agricoles, pouvant être vues par certains acteurs comme de vraies opportunités foncières.

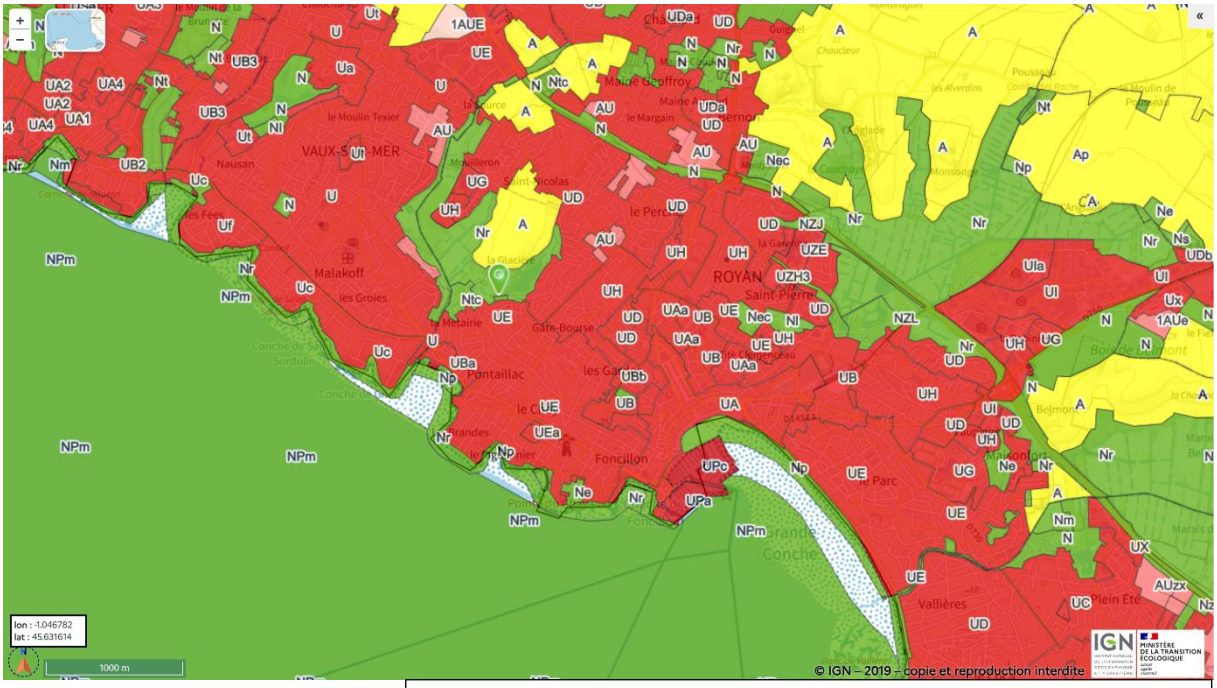

Production Mehdi AMROUNE – modèle carte : Géoportail Urbanisme ; données : Ministère de la transition écologique